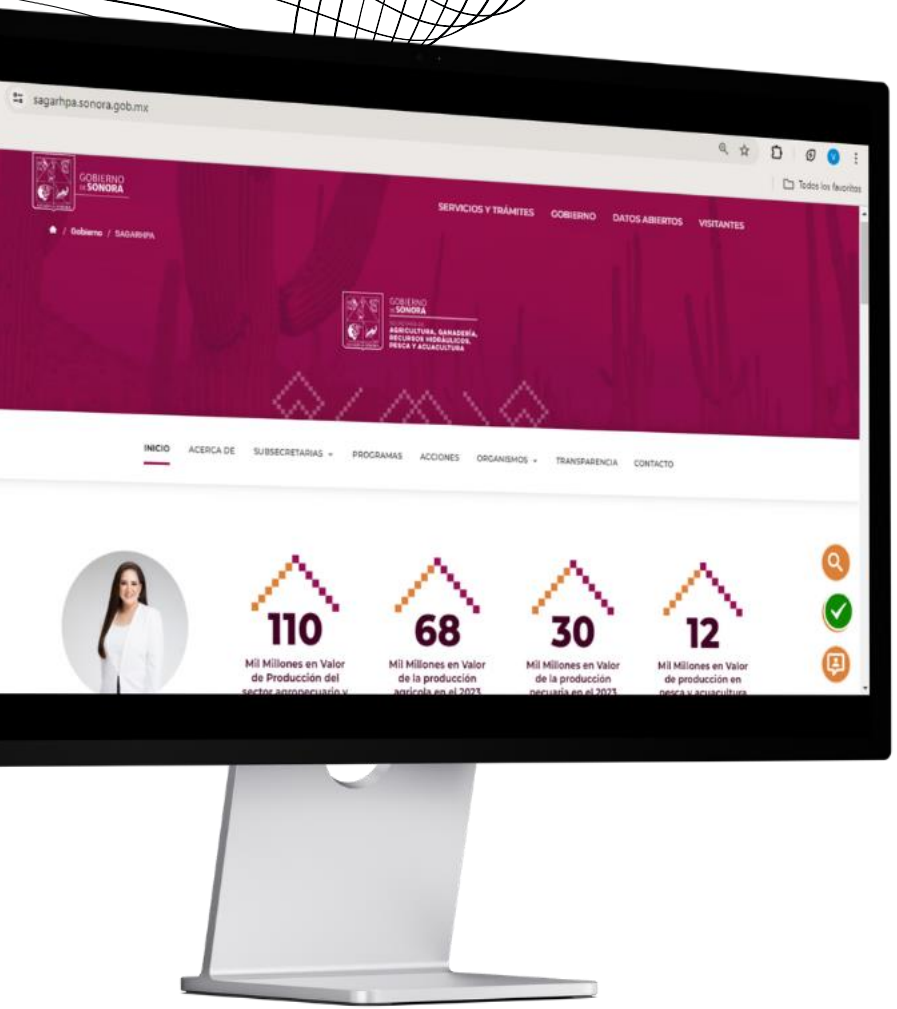

Dirección de

Estadística y Tecnologías

SONORA TIERRA DE OPORTUNIDADES

GOBIERNO DE SONORA
SECRETARÍA DE AGRICULTURA, GANADERÍA, RECURSOS HIDRÁULICOS, PESCA Y ACUACULTURA

SAGARHPA

MISIÓN

Fomentar la modernización continua y desarrollo sustentable Agropecuario, forestal, pesquero y acuícola, elevando la calidad de vida que demanda la población de las distintas regiones del Estado de Sonora.

VISIÓN

Ser una dependencia de excelencia, que transforme las actividades agropecuarias, forestales, pesqueras y acuícola del Estado de Sonora.

ORGANISMOS

IAES Instituto de Acuacultura del Estado de Sonora, O.P.D.

FFRS Fideicomiso Fondo Revolvente Sonora

OIAPES

CEA COMISIÓN ESTATAL DEL AGUA

FIDEICOMISO MAESTRO PARA EL FINANCIAMIENTO DEL SECTOR AGROPECUARIO EN SONORA AGROSON

ESTADÍSTICA

Banco de Información Agropecuaria, Pesquera y Acuícola

Producción y Valor del Sector Primario del Estado de Sonora

Reporte de cierre de mercados

Registro de precios de productos del sector primario en mercados nacionales e internacionales.

Análisis del Sector Primario

interpretación de la información con posterior difusión a través de tarjetas informativas.

Registro de Precipitaciones y Almacenamiento de Presas

Cuantificación y registro diario del almacenamiento de presas y condiciones climáticas del Estado

Indicadores Macroeconómicos

Comportamiento de la Balanza Comercial, Población Económica y Asegurados del IMSS

GOBIERNO DE SONORA
SECRETARÍA DE AGRICULTURA, GANADERÍA, RECURSOS HIDRÁULICOS, PESCA Y ACUACULTURA

SAGARHPA no solo ejecuta programas, también analiza datos para decidir mejor.

SONORA
TIERRA DE OPORTUNIDADES

ÁREA DE TECNOLOGÍAS

Ley de Gobierno Digital

Seguimiento de Infraestructura Tecnológica y de Telecomunicaciones

Elaboración del Plan para la Gestión de Incidentes de Seguridad Informática

Página web de Sagarhpa y enlace con organismos

Digitalización de trámites y servicios con la colaboración del grupo de trabajo ITH

Capacitación en TIC's y temas referentes a la información del sector

Gestión administrativa

- Alta/ Baja de correos institucionales
- Dictámenes técnicos

TABLEROS ESTADÍSTICOS PORTAL SAGARHPA

Agricultura

Ganadería

Capacidad Hídrica

Pesca

DASHBOARD DISPONIBLES

Precipitaciones en el Estado de Sonora

Subastas de Ganado en Hermosillo

CONVENIOS

SADER
SECRETARÍA DE AGRICULTURA Y DESARROLLO RURAL

inifap

SIAP
SERVICIO DE INFORMACIÓN AGROALIMENTARIA Y PESQUERA

- Mayor Precisión y Confiabilidad en los Datos
- Datos Actualizados y en Tiempo Real
- Identificación de Tendencias y Patrones
- Base de Conocimiento para Investigación

TECNOLÓGICO NACIONAL DE MÉXICO

- Convenio para realizar las residencias profesionales, servicio social.
- Intercambio de información.
- Uso de instalaciones.

INSTITUCIONES GENERADORAS

INEGI

Se obtiene información relacionada a la población.

AOANS

Información referente a las cosechas en la temporada.

SAT

Se obtiene Información financiera relacionada con el sector primario.

UNION GANADERA REGIONAL DE SONORA

Se obtiene información relacionada a las cabezas de ganado en el estado.

INSTITUCIONES GENERADORAS

FIRA
FIDEICOMISOS INSTITUIDOS EN RELACION CON LA AGRICULTURA

Información acerca de la economía de los productores del sector primario.

CESAVE

Información fitosanitaria, es un auxiliar de SADER.

CONAGUA
COMISIÓN NACIONAL DEL AGUA

Se obtiene información relacionada con el almacenamiento de presas y precipitaciones en el estado.

ÁREA CIENCIA DE DATOS

Análisis predictivo

Utilizar modelos estadísticos y de machine learning para predecir rendimientos de cultivos, patrones de lluvia, plagas, y otras variables clave.

Big Data e Integración de Datos

Integrar y analizar grandes volúmenes de datos provenientes de diversas fuentes, como satélites, sensores IoT, y bases de datos gubernamentales.

Monitoreo y Evaluación

Desarrollar sistemas de monitoreo para evaluar el impacto de políticas y programas, mejorando su efectividad y eficiencia.

Toma de decisiones

Analizar datos para optimizarla toma de decisiones para la creación de políticas públicas promoviendo prácticas sostenibles y eficientes.

Visualización de Datos

Crear dashboards y reportes interactivos que permitan acceder a información crítica de manera rápida y comprensible.

RETOS ACTUALES | SOLUCIÓN PARA EL MAÑANA

SECTOR AGROPECUARIO Y PESQUERO

SITUACIÓN ACTUAL

INDIVIDUALISMO

BAJA PRODUCTIVIDAD

DESVENTAJA COMERCIAL

SOLUCIONES

ASOCIATIVIDAD

ACCESO A LA INFORMACIÓN

TECNOLOGÍA Y CAPACITACIÓN

FINANCIAMIENTO Y ASESORÍA

PROMOVER EL VALOR AGREGADO

CALENDARIO AGRÍCOLA CICLO 2025-26

Estado de Sonora

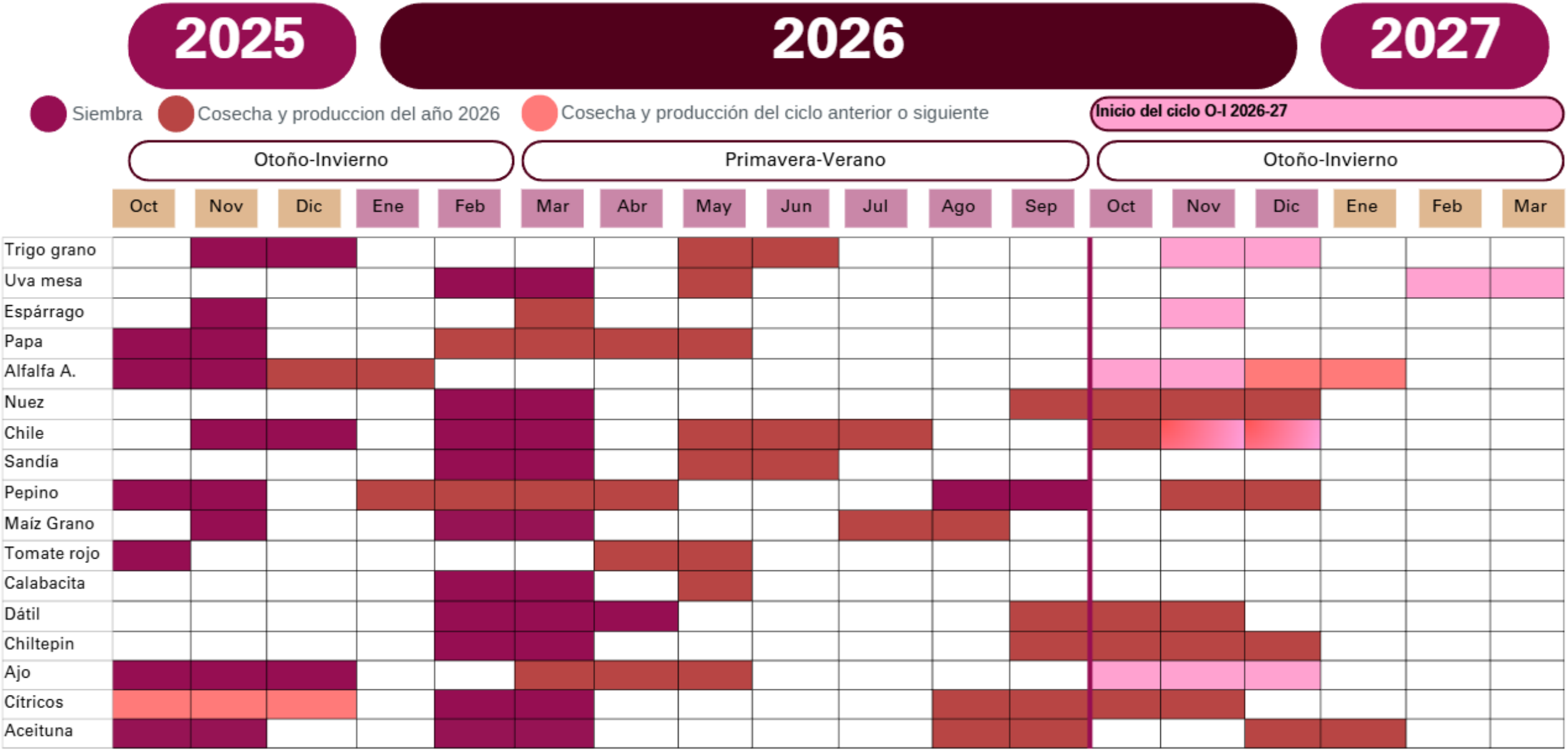

PRINCIPALES CULTIVOS POR DISTRITOS DE DESARROLLO RURAL Y DISTRITOS DE RIEGO EN SONORA

DISTRITOS DE DESARROLLO RURAL

139 Caborca	*Espárrago, Papa, Uva*
140 Magdalena	*Papa, Alfalfa, Tomate (jitomate)*
141 Agua Prieta	*Forrajes, Papa, Chile Verde*
142 Ures	*Forrajes, Ajo, Nuez*
143 Moctezuma	*Forrajes, Nuez, Maíz Grano*
144 Hermosillo	*Uva de Mesa, Nuez, Garbanzo*
145 Mazatán	*Forrajes, Nuez*
146 Sahuaripa	*Forrajes, Maíz Grano, Frijol*
147 Guaymas	*Uva de Mesa, Chile, Calabacita*
148 Cajeme	*Forrajes, Trigo Grano, Papa*
149 Navojoa	*Trigo grano, Maíz Grano, Papa*
193 San Luis RC	*Espárrago, Dátil, Forrajes*

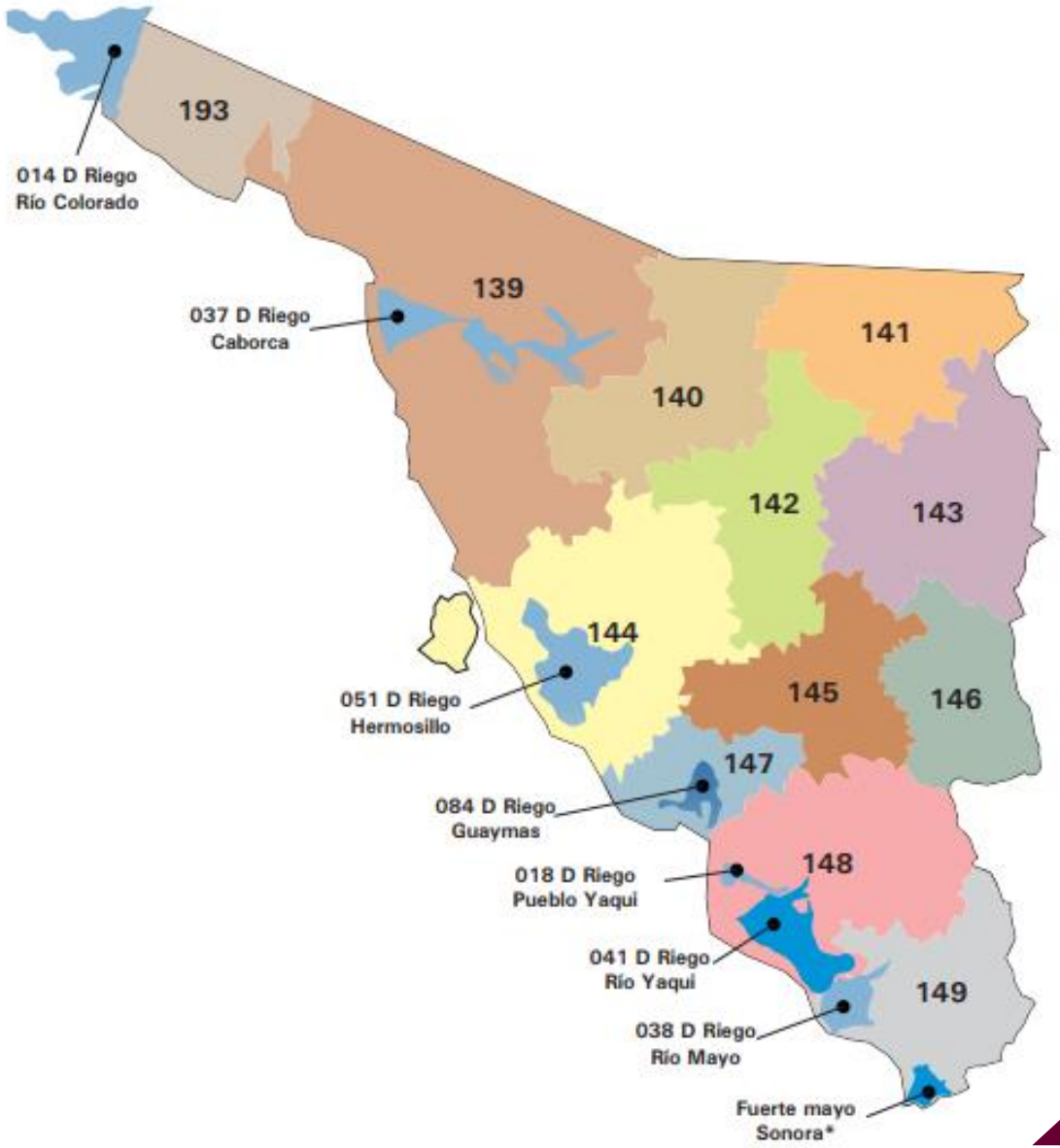

PORCENTAJE CON ALGUNA TECNIFICACION DE RIEGO DISTRITOS DE RIEGO EN SONORA

Aspersión

Rodado

Línea de conducción

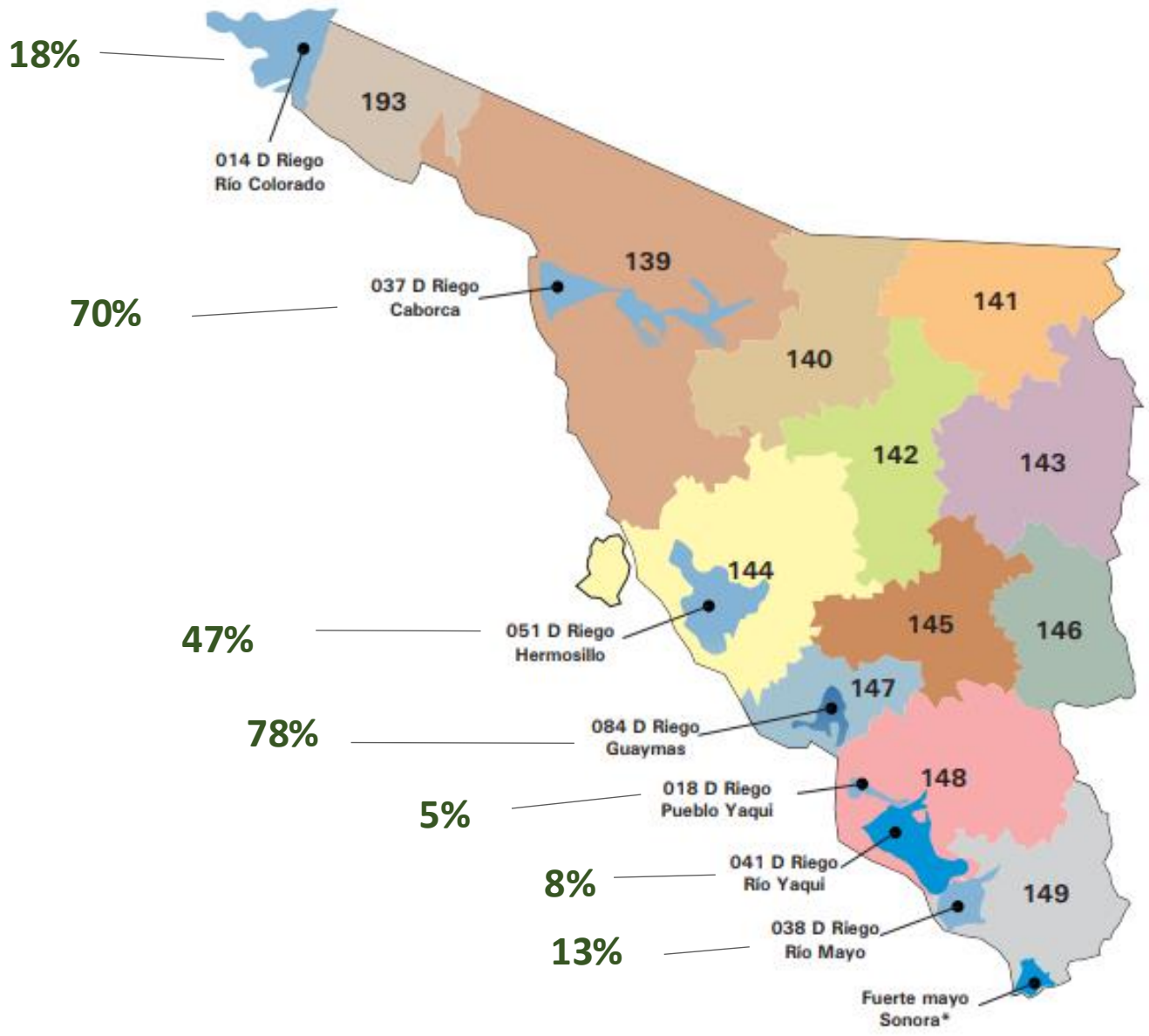

Pozo

Presa

Cultivo	Tipo	Ciclo	Riego	Lámina (cm)	m³/ha	Huella (mil m³/ha)	Rend. t/ha	m³/ton	Utilidad $/ha	Reconversión	Comentario
Trigo	Básico	OI	Gravedad	83.6	7,500	7.5	6.8	1,103	9,818	Baja	Alto consumo hídrico por escala
Cebada	Básico	OI	Gravedad	55	6,000	6	7.7	779	20,164	Media	Vinculación potencial industria
Cártamo	Oleaginosa	OI	Gravedad	45	4,800	4.8	1.93	2,487	4,053	Alta	Alternativa OI de menor presión hídrica
Garbanzo	Leguminosa	OI	Gravedad	40	4,000	4	2.2	1,818	5,404	Alta	Menor demanda hídrica
Guar	Industrial	PV	Gravedad	40	4,000	4	2	2,000	8,500	Alta	Segundo cultivo
Higo	Perenne	Perenne	Gravedad	25	2,500	2.5	3	833	7,000	Alta	Perenne, baja huella
Frijol	Leguminosa	OI	Gravedad	40	4,000	4	2.05	1,951	10,200	Media	Ciclo corto
Papa	Hortaliza	OI	Tecnificado	80	8,000	8	36	222	49,000	Baja	Alta rentabilidad, alto costo
Chile Jalapeño	Hortaliza	OI	Goteo	—	5,684	5.7	44	129	—	Media	Alta eficiencia hídrica
Chile Jalapeño	Hortaliza	OI	Tradicional	—	8,206	8.2	44	187	—	Baja	Mayor consumo
Calabaza	Hortaliza	OI	Goteo	—	6,277	6.3	20	314	—	Media	
Tomate rojo	Hortaliza	OI	Goteo	—	7,829	7.8	60	130	—	Media	
Tomate verde	Hortaliza	OI	Goteo	—	7,653	7.7	55	139	—	Media	

¿Cuánta agua requiere el trigo en Sonora?

- Superficie sembrada de trigo: 250,000 hectáreas
- Producción estimada: 1.7 millones de toneladas (7.0 ton/ha)

Conversión a unidades “macro”

- 1,875 Mm^3 (millones de m^3)
- 1.88 km^3 de agua
- 1.9 billones de litros de agua
- 1,100 m^3 de agua por tonelada de trigo (0.0011 hm3)



- Información precisa y confiable
- Conocer tendencias
- Contar con el apoyo gubernamental

- Producto de calidad
- Tiempos exactos
- Tema Sanitario

Desde SAGARHPA, el análisis de datos nos permite responder tres preguntas clave ***¿qué sembrar?, ¿dónde sembrar? y ¿para quién sembrar?****, considerando agua, mercado y viabilidad.*